ניתוח אתר וסביבה

קיסריה · רובע 13 (שכונת הגולף) · אקלים, תכנון ואסטרטגיות

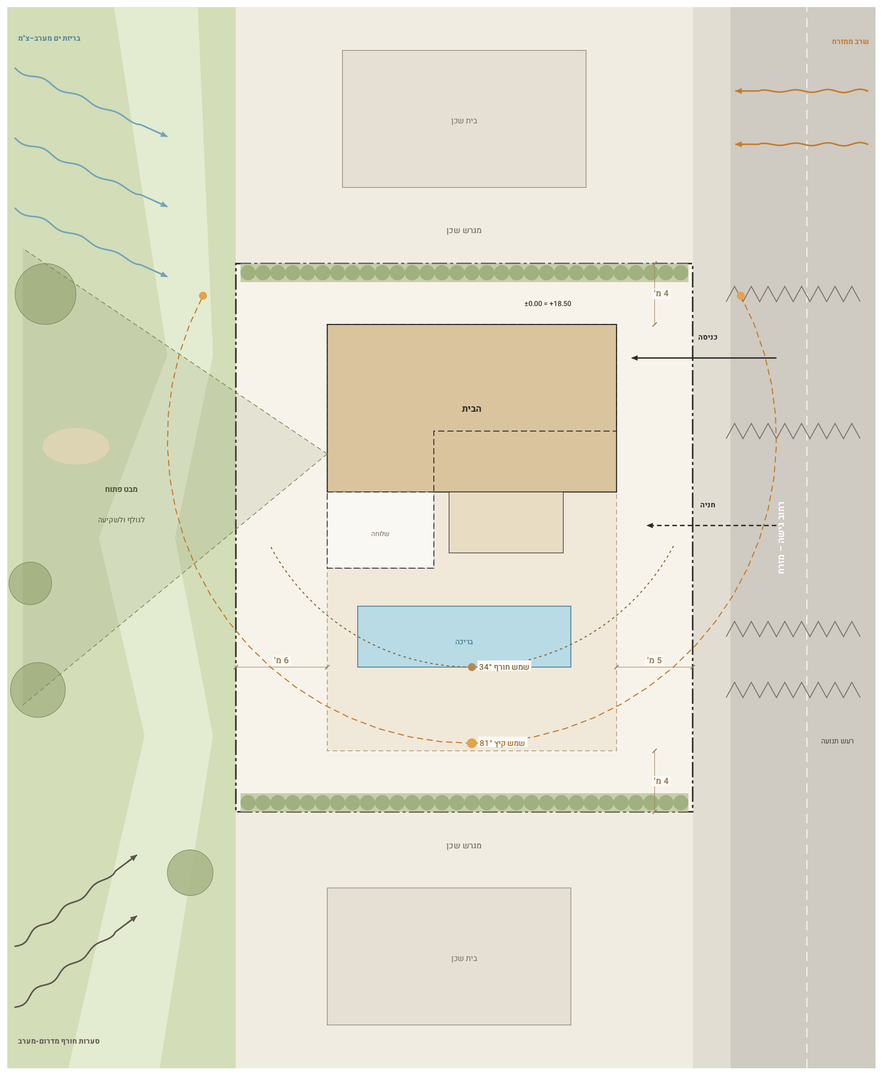
01 קיסריה – סכמת העיר וסביבתה

סכמה – לא בקנה מידה



מיקום השכונות והגולף מכתבי בלבד

02 ניתוח המגרש – רובע 13



מקרא

- ברזיות ים קיצית מערב–צפון-מערב
- סערות חורף מדרום-מערב
- שרב – רוח מזרחית חמה ויבשה
- מסלול שמש – קיץ (21.6)
- מסלול שמש – חורף (21.12)
- מבט פתוח לגולף ולשקיעה
- רעש תנועה מן הרחוב
- מיסוך צמחייה – פרטיות
- קווי בניין – תחום בנייה
- גבול מגרש 30×36 מ'

שטח המגרש	1,080 מ"ר
חזית לרחוב	30 מ' (מזרח)
עומק	36 מ'
גבול מערבי	מגרש הגולף
מפלס ±0.00	18.50+ מעל פני הים

03 אסטרטגיות תכנון – מן הניתוח אל הבית

01 אוריינטציה

ציר ארוך מזרח–מערב, חללי המגורים והוויטרינות פונים דרומה אל הגן, חזית הרחוב במזרח סגורה ושקטה.

ביישום: סלון, אוכל ומטבח בחזית הדרומית, לובי, שירות וחניה במזרח.

02 הצללה דרומית

שלוחה של 5 מ' ולוג'יה שקועה 1.6 מ' – הוסמות את שמש הקיץ (81°) ומכניסות את שמש החורף (34°).

ביישום: מרפסת מקורה של 35 מ"ר מתחת לשלוחה; לוג'יית ההורים.

03 רפפות מערביות

רפפות אנכיות 50/200 מ"מ במרווח 180 בחזית המערבית חוסמות את שמש אחר-הצהריים הנמוכה ושומרות על המבט לגולף.

ביישום: חזית מערב של פוטיות ההורים וחזית מזרח של חדר שינה 2.

04 אוורור צולב וארובה

פתחים מנוגדים בכיוון ברזית הים, ופליטת אוויר חם דרך חדר המדרגות והציר הגבוה ביותר.

ביישום: וויטריות הזזה בדרום ובמערב, דיגום רציף בחדר המדרגות.

05 חומרים לאוויר מלוח

אלומיניום בגימור ימי, נירוסטה 316, אבן טבעית ספוגה, טיח סיליקטי; פרטי איטום וניקוז מוגברים.

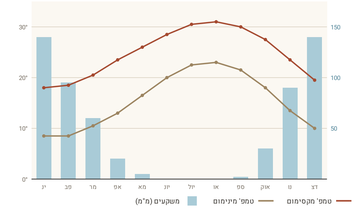
ביישום: פרזול נירוסטה 316, אלומיניום בצבעיה בתנור בדרגה ימית.

06 אנרגיה ומים

מערכת PV על הגג (חובה), דוד שמש, השקיה בטפטוף וצחיחיה ים-תיכונית מסכונית במים.

ביישום: פאנלים על גג האגף המערבי; מרפסת גג עם פרגולה.

04 נתוני אקלים



טמפ' ממוצעת יולי–אוגוסט	23° / 31°
טמפ' ממוצעת ינואר	8.5° / 18°
לחות יחסית	65%–75% (גבוהה בקיץ)
משקעים שנתיים	כ-580 מ"מ, נוב'–מרץ
רוח שלטת	מערב–צ"מ, 3–5 מ'/שנ'
קרינת שמש	כ-2,000 קוט"ש/מ"ר·שנה
אוויר	מלוח – כ-2 ק"מ מן הים

ערכים משוערים – מיושר לתוף הפנימי (תדרה/קיסריה), לפי ממוצעי הטווחות המסאורלוגי.

05 נתוני תכנון – הנחת בסיס

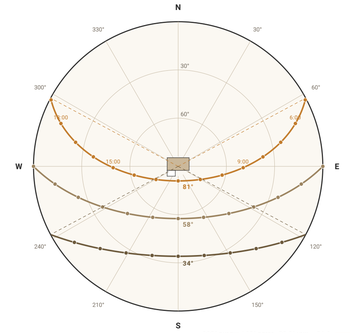
נושא	רובע 13	מוצע
שטח מגרש	1,080 מ"ר	1,080 מ"ר
שטח עיקרי	35% = 378 מ"ר	ניליין 04
שטחי שירות	16% = 173 מ"ר	ניליין 04
תכסית	40% = 432 מ"ר	244 מ"ר = 22.6%
קומות	2 + מרתף	2 + מרתף + גג
מרתף	בקונטור קומה מעל	בקונטור
קו בניין קדמי (מזרח)	5 מ'	5 מ'
קווי בניין צדדיים	4 מ'	4 מ'
קו בניין אחורי (מערב)	6 מ'	6 מ'
חניה	2 בתחום המגרש	2 מקורות
בריכה – שטח מים	עד 60 מ"ר	56 מ"ר
בריכה – עומק	עד 1.8 מ'	1.45 מ'
משרבת PV על הגג	חובה	מתוכנן

יש לאשת מול תב"ע 303-0207092

וו-טסח הביניי של רובע 13 למני הגשה לוועדה המקומית חוף הכרמל.

תקנות מדרגות: 2R+T = 61–63 ס"מ, רום עד 17.5; משקה 105 ס"מ; מח"ר טוו 9 ס"מ לפחות; גובה חדר מגורים 2.50 מ' לפחות.

06 מסלול השמש – 32.5° צפון



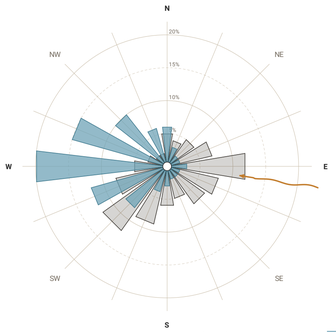
21.6 – שיא 80.9° · זריחה 62° / שקיעה 298°

21.3 / 23.9 – שיא 57.5° · זריחה 90° / שקיעה 270°

21.12 – שיא 34.1° · זריחה 118° / שקיעה 242°

הטיל קוטבי – אזימוט מצפון, רדיוס = 90° פיתוח נוכח השמש.

07 שושנת רוחות



קיץ – ברזית ים מערב–צפון-מערב (צהריים)

חורף – סערות מדרום-מערב, רוח יבשה מזרחית

שרב – מזרח/דרום-מזרח, אביב וסתיו

תדירות משוערות לפי עונה – סכמה להמחשה.

בית כורכר

BEIT KURKAR

שם הפרויקט:
וילת בוטיק בקיסריה

מיקום הפרויקט:
קיסריה, רובע 13 (מגרש לימודי)

מנחה:
שירן שריקי

שם הגיליון:
ניתוח אתר וסביבה

מס' גיליון: **03**

קנ"מ: **–**

רשימת גיליונות:

01	שער	
02	קונספט ומחקר	
03	**ניתוח אתר וסביבה**	
04	תכנית הנחת הבסיס ושטחים	1:200
05	תכנית פיתוח עקרוני	1:100
06	תכניות מרתף וקרקע	1:100
07	תכניות קומה א' וגג	1:100
08	חזיתות	1:100
09	חתכים	1:100
10	סכמות מסטיות	1:100
11	תכנית קומת קרקע	1:50
12	תכנית קומה א'	1:50
13	חזיתות	1:50
14	חתך A-A	1:50
15	חתך B-B	1:50
16	ניליין מדרגות	1:25, 1:5
17	פרטי בניין	1:20, 1:5
18	רשימת אלומיניום וזגוגות	1:50
19	עיצוב פנים – חלל המגורים	1:50
20	עיצוב ריהוט – אי-המטבח	1:25, 1:10, 1:2
21	הדמיות חוץ	
22	הדמיות פנים	
23	תודה	

מנחה:
הנדסאים – אדריכלות ועיצוב פנים

שם המגיש/ה ות.ז.:
_____ _____

תאריך:
10.2026

